Strätscherhorn

Schwierigkeit:
Kondition:
Popularität:

Distanz: 9.8 km
Zeitbedarf: 6:00 h

Aufstieg: 893 m
Höchster Punkt: 2567 m.ü.M.

Region: Safiental Rheinschlucht
Startpunkt: Safien Thalkirch Turrahus

Tourenbeschreibung

Nicht nur ein bekannter Skitourengipfel, sondern auch eine lohnende Tour für Schneeschuhgänger. Von Turrahus hinauf über die Alp Falätsch und Älpli oder über den Tomülpass zum Strätscherhorn. Abstieg direkt via Alp Piänetsch und Piggamad reotour nach Turrahus.

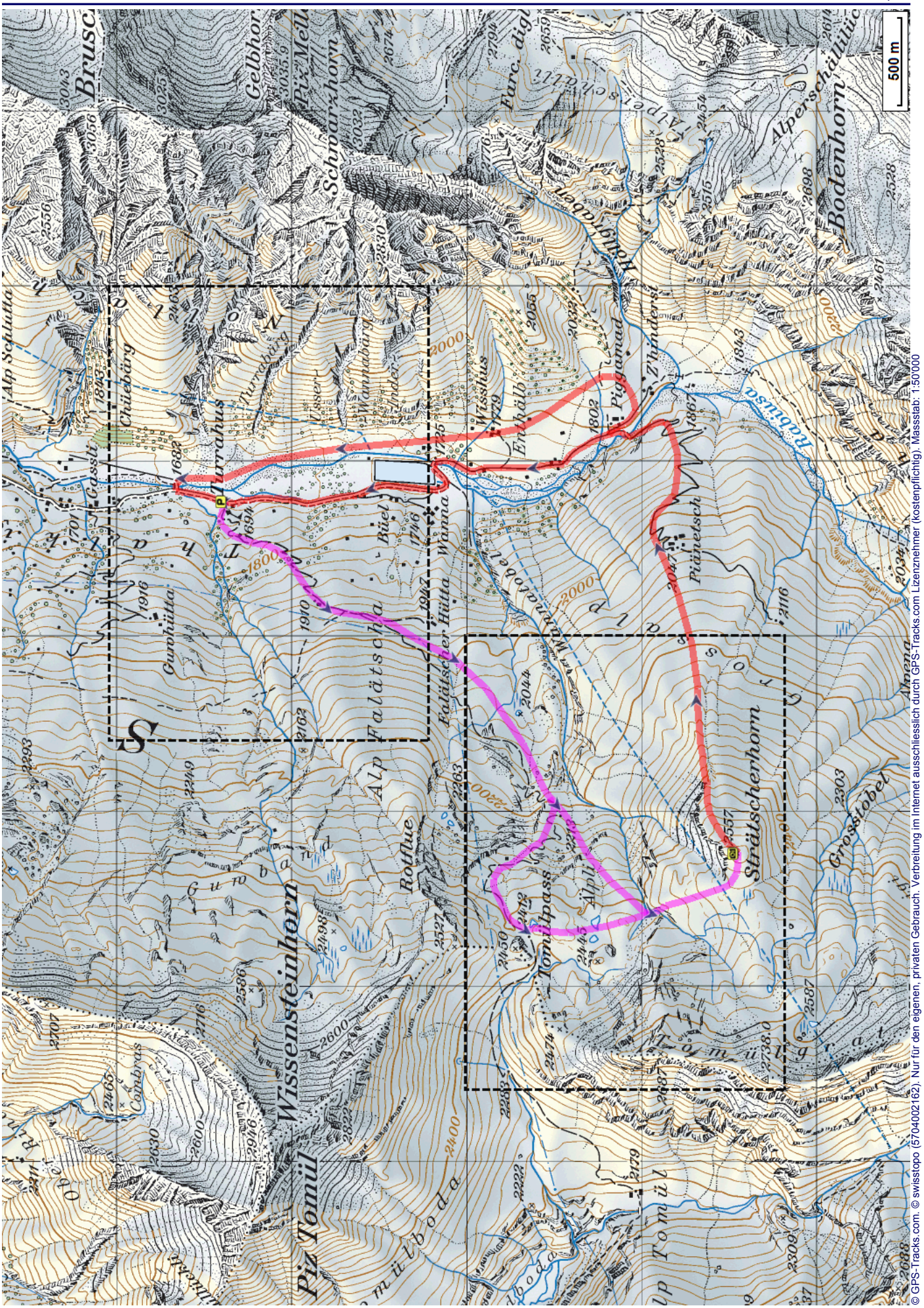
Orte an der Route

Turrahus - Alp Falätscha - Älpli - Strätscherhorn - Alp Piänetsch - Piggamad - Turrahus

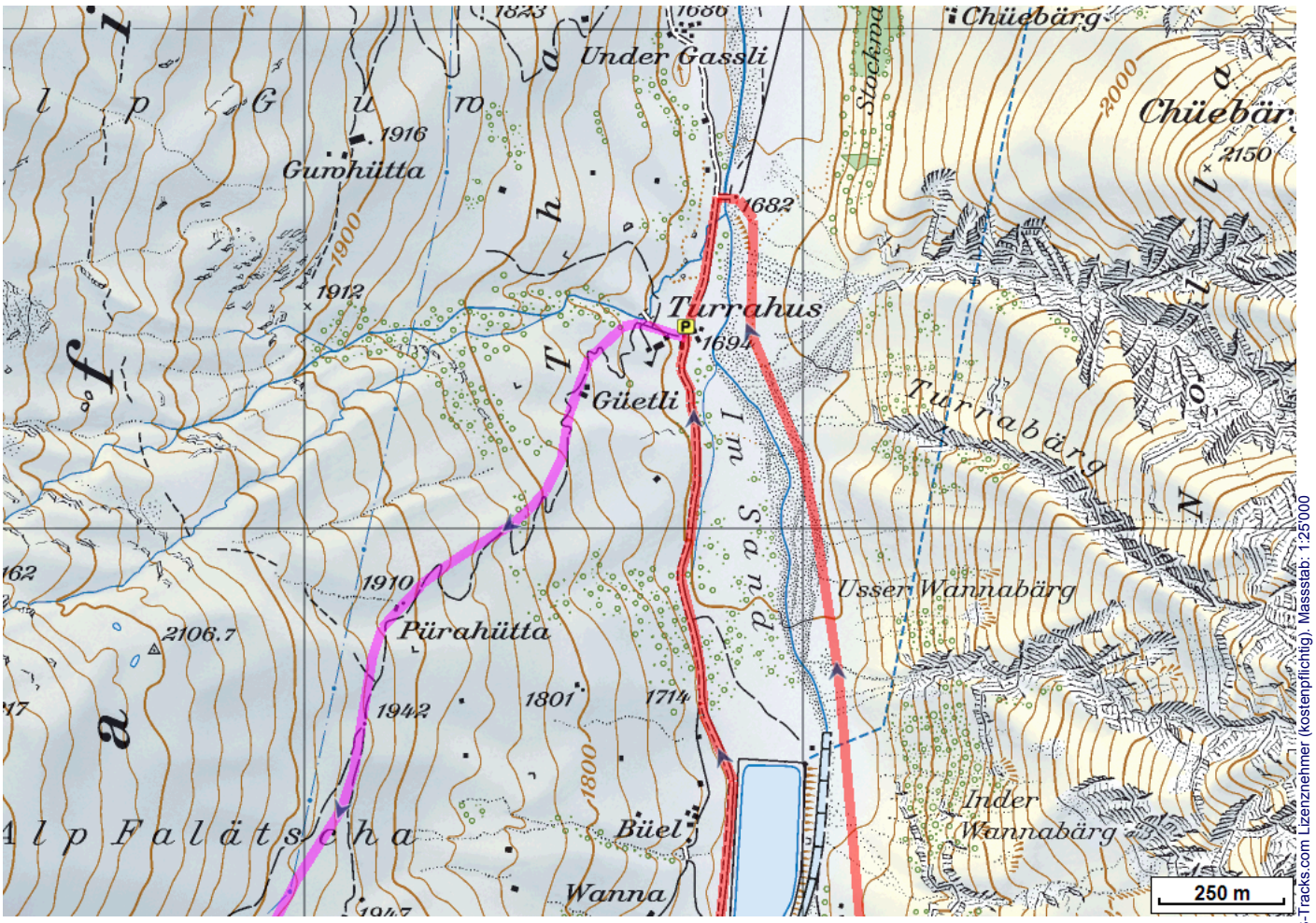
Variante(n)

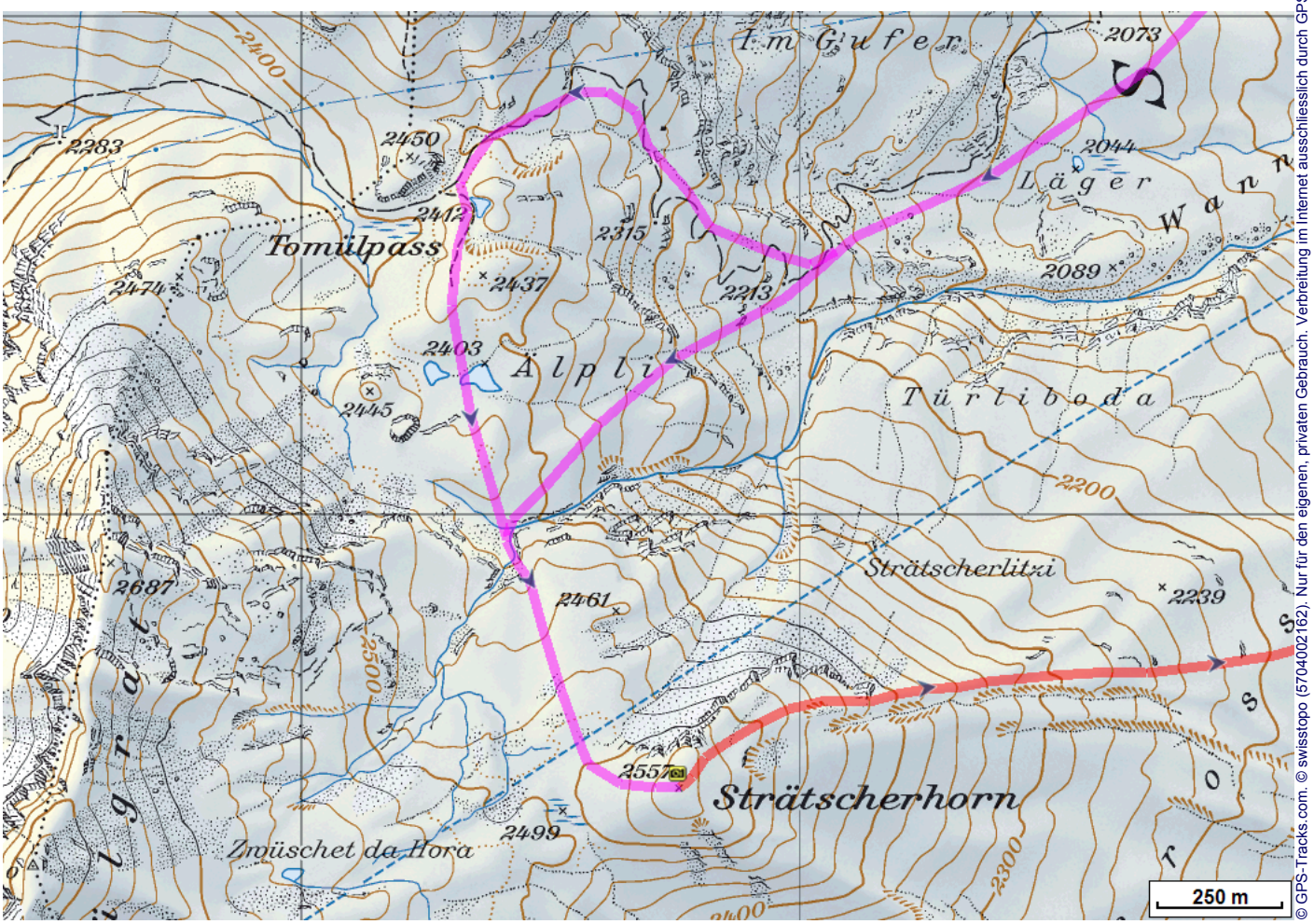
Variante A: Kleine Rundtour zum Talabschluss, dann über Enthälb zurück nach Turrahus (2 Std. / Schwierigkeit leicht).

Strätscherhorn


500 m
Strätscherhorn
Wissensteinhorn
Piz Tomül
Rotflue
Tomülpass
Alp Falätscha
Alp Tomül
Grosstobel
Bodenhorn
Piz Mellen
Gelbhorn
Schwarzhorn
Alp Schlutta
Chüeberg
Furrahus
Wissihus
Pigganad
Zhinders
Pfiffetsch
Wanna
Biel
Gurohütta
Hütta
Wannabärg
Almena
Alperschällilücke
Radbuusa
Tomülpass
Alpli
Combras
Tomül
Grat
Ob. Tomülboda
Ob. Tomülboda
Ob. Tomülboda

Strätscherhorn

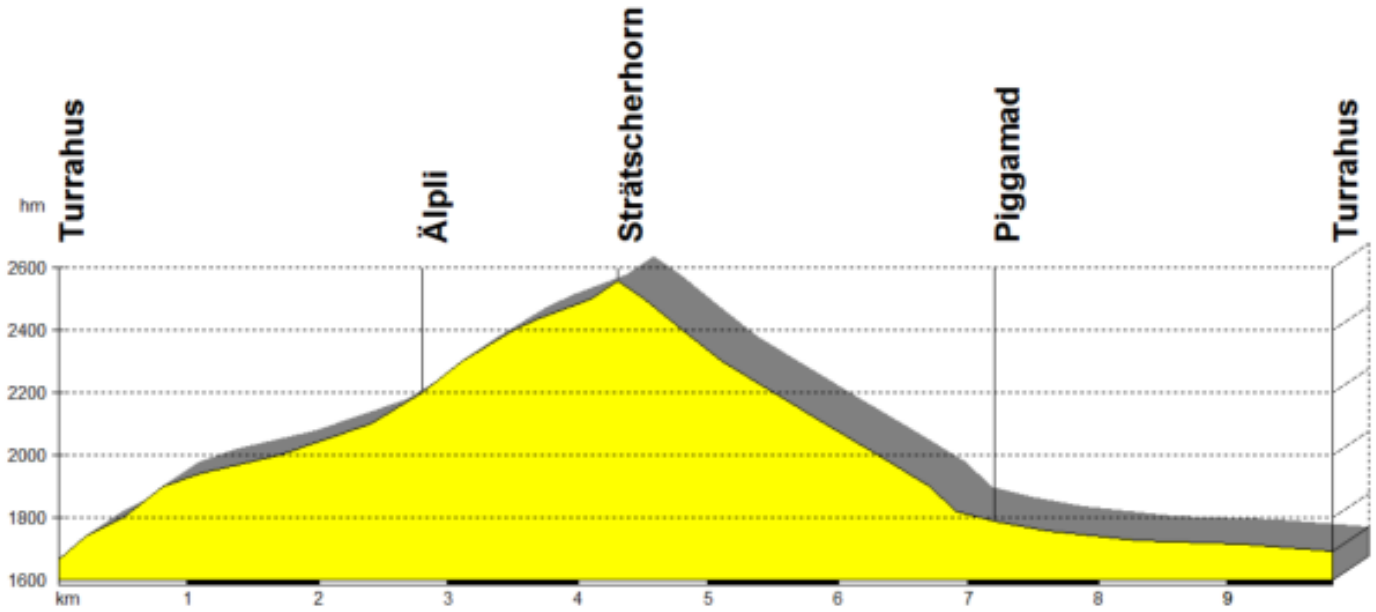




© GPS-Tracks.com © swisstopo (5704002162). Nur für den eigenen, privaten Gebrauch. Verbreitung im Internet ausschliesslich durch GPS-Tracks.com Lizenznehmer (kostenpflichtig). Massstab: 1:25000

Strätscherhorn

Höhenprofil



Wetter im Gebiet ab dem 13.02.2013

Mittwoch
Heiter. Höchsttemperatur: 3C. Windgeschwindigkeit: 10-20 km/h. Windrichtung: Nord.

Donnerstag
Wolkig. Höchsttemperatur: 7C. Leichter Wind.

Freitag
Schnee möglich. Höchsttemperatur: 5C. Windgeschwindigkeit: 10-15 km/h. Nord-Nordwest. Regenrisiko 50%.

Samstag
Teils Wolkig. Höchsttemperatur: 9C. Windgeschwindigkeit: 5-15 km/h. Windrichtung: Nord.

Tour erstellt am: 12.01.2012

Letzte Tourenänderung: 27.03.2012

Quelle: GPS-Tracks.com

Die Routenführung von Ski-, Schneeschuh- und Alpintouren liegt meistens ausserhalb von markierten Wegen. Die Linienführung dient als Planungsgrundlage. Je nach den lokal anzutreffenden Verhältnissen sind abweichende Teilstrecken zu wählen.
Der Aufenthalt auf nicht markierten / kontrollierten Pisten kann aufgrund von Absturz- und Lawinengefahr sowie Gletscherspalten lebensgefährlich sein. Unfälle können nicht ausgeschlossen werden.
Inhalte und Touren sind nach bestem Wissen zusammengestellt, eine Gewähr für die Richtigkeit der Angaben kann nicht gegeben werden. Die Begehung der Tour erfolgt auf eigene Verantwortung. Bei allfälligen Schäden wird jegliche Haftung seitens des Publizisten, des Autors oder der Grundeigentümer der Tour abgelehnt.